Analyse du marché immobilier français

et identification des opportunités d’investissement

Thomas Giffaux
Data Analyst Projet Portfolio

[Python / Power BI / Open Data]

Contexte du projet

Le marché immobilier français est très hétérogène. Les prix, les loyers et les rendements varient fortement selon les territoires. Dans ce contexte, identifier les communes réellement attractives pour un investissement immobilier peut être complexe. L’objectif de ce projet est justement d’utiliser la donnée pour mieux comprendre ce dynamique et identifier les opportunités d’investissement.

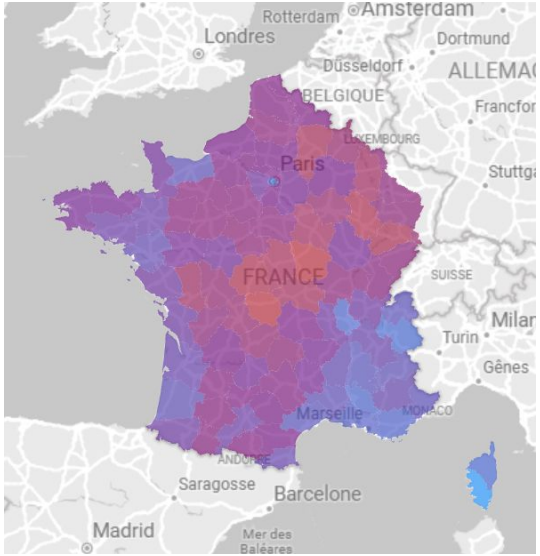

Objectif du projet

L'objectif du projet est d'identifier les communes offrant les meilleures opportunités d'investissement immobilier. Pour cela j'ai analysé le marché immobilier selon deux stratégies principales.

Investissement locatif

↓

maximiser le rendement locatif

Indicateurs utilisés :

- rendement locatif
- niveau de loyers
- liquidité du marché

Investissement patrimonial

↓

privilégier la valorisation du capital à long terme

Indicateurs utilisés :

- croissance des prix immobiliers
- niveau de valorisation du marché
- dynamique démographique

L'analyse repose sur la construction de scores d'investissement et se matérialise par un dashboard interactif permettant d'explorer les opportunités immobilières.

Sources de données

Pour analyser le marché immobilier, j'ai utilisé plusieurs sources de données publiques. La base principale est la base DVF qui recense les transactions immobilières en France. Je l'ai enrichie avec des données de loyers issues du ministère du logement et des données démographiques provenant de l'INSEE. L'ensemble des données a ensuite été agrégé au niveau communal pour permettre l'analyse territoriale.

Loyers immobilier

DHUP - Ministère du Logement
(2022 - 2024)

- loyers estimés au m²
- segmentation par type de bien

Transaction immobilières

DVF - Demandes de Valeurs Foncières
(2021 - 2024)

- transactions immobilières
- prix de vente des biens
- surface et type de bien
- localisation par commune

Données démographique

INSEE
(2020 - 2023)

- population communale
- évolution de la population

Préparation des données

Nettoyage des données

suppression des valeurs aberrantes

gestion des valeurs manquantes

Harmonisation des identifiants géographiques

utilisation du code INSEE comme clé commune

création du code département

Agréation des données

Commune **x** Année **x** Segment de bien

.Appartement 1-2 pièces
.Appartement 3 pièces et +
.Maison

Construction des indicateurs immobiliers

.prix immobilier médian au m²
.loyer médian au m²
.rendement locatif brut
.nombre de ventes
.croissance démographique

Analyse du marché immobilier

L’analyse exploratoire met en évidence une forte dispersion des prix immobiliers en France. les prix au m² varient fortement selon les territoires avec :

- une majorité de communes entre 1 000 € et 4 000 € / m²
- certaines zones très valorisées dans les grandes métropoles

Les loyer présentent une dispersion plus faible que les prix immobiliers. Les rendement locatifs observés se situent généralement entre 4 % et 7 %.

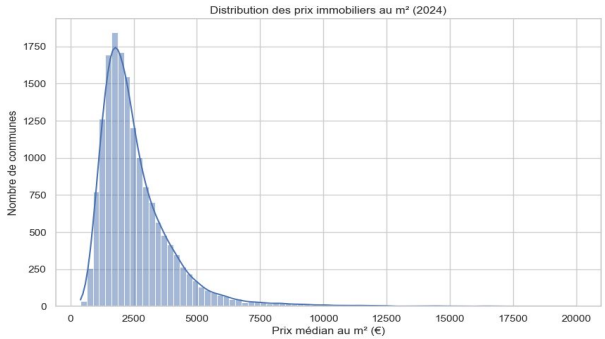

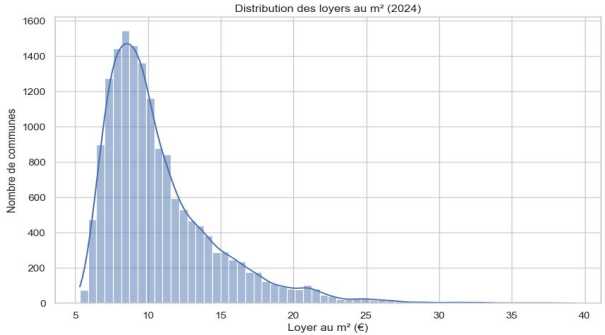

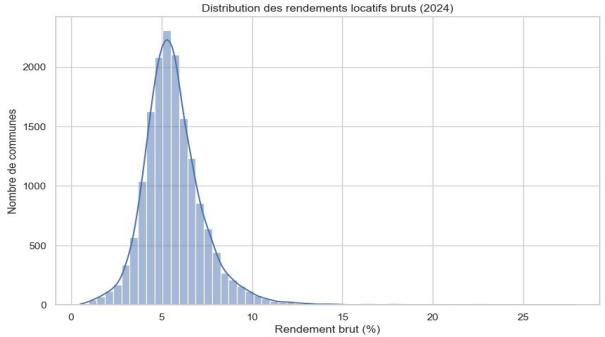

Différences selon le type de bien

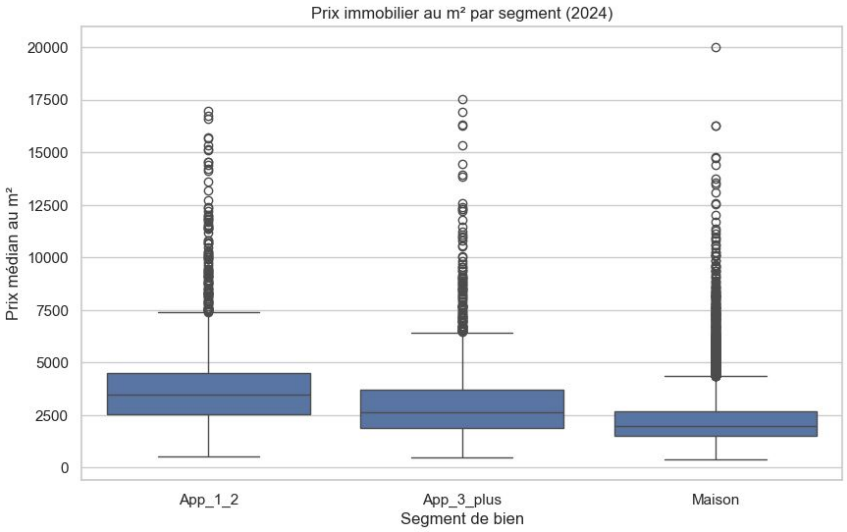

L'analyse met en évidence des différences importantes de prix au m² selon le type de logement :

- Appartement 1-2 pièces ~ 3 500 € / m²
- Appartement 3 pièces et plus ~ 2 700 € / m²
- Maison ~ 2 000 € / m²

Les petites surfaces présentent généralement un prix au m² plus élevé. Cela s'explique par :

- une forte demande locative
- un prix d'acquisition plus accessible pour les investisseur
- une rentabilité locative souvent plus élevé

A l'inverse, les maisons disposent généralement :

- d'une surface plus importante
- d'un prix au m² plus faible

Analyse territoriale du marché immobilier

L’analyse géographique met en évidence de fortes disparités territoriales sur le marché immobilier français.

Les prix immobiliers varient fortement selon les territoires, notamment entre :

- les grandes métropoles
- les zones littorales
- les territoires ruraux

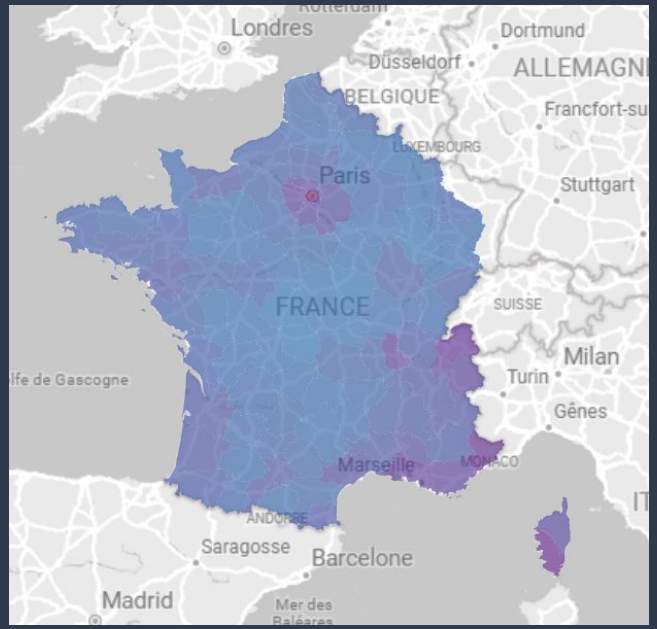

Les territoires les plus valorisés si situent généralement :

- dans les grandes agglomérations
- dans les zones à forte attractivité économique
- dans certaines zones touristiques

Construction des scores d’investissement

Afin d’identifier les communes les plus attractives pour l’investissement immobilier, plusieurs scores d’investissement ont été construits à partir des indicateurs du marché. Ces scores permettent de combiner plusieurs dimensions du marché immobiliers :

- rentabilité locative
- dynamique du marché
- valorisation patrimoniale

Score locatif

Identifie les communes offrant les meilleurs rendements locatifs.

Variables utilisées :

- rendement locatif
- niveau des loyers
- volume de transaction

Score patrimonial dynamique

Identifie les territoires où les prix immobiliers augmentent le plus.

Variables utilisées :

- croissance des prix
- croissance démographique
- volume de transaction

Score patrimonial valeur

Identifie les marchés immobilier premium

Variables utilisées :

- prix immobilier au m²
- croissance démographique
- volume de transaction

Score global d’investissement

Afin d’identifier les communes présentant le meilleur potentiel d’investissement, un score global a été construit en combinant les différents scores d’analyse. Le score global intègre trois dimensions principales du marché immobilier :

- rentabilité locative
- dynamique du marché
- valorisation patrimoniale

Le score global est calculé selon la pondération suivante	
Score	**Pondération**
Score locatif	40 %
Score patrimonial dynamique	30 %
Score patrimonial valeur	30 %

Les communes présentent un score global élevé sont généralement caractérisées par :

- un bon rendement locatif
- une dynamique de marché positive
- un potentiel de valorisation patrimoniale

ces territoires représentent les meilleurs opportunités d’investissement immobilier.

Dashboard d’analyse immobilière

Un dashboard interactif Power BI a été développé afin de permettre l’exploration des données immobilières et l’identification des opportunités d’investissement. Ce dashboard permet d’analyser le marché immobilier français, comparer les territoires et identifier les communes les plus attractives.

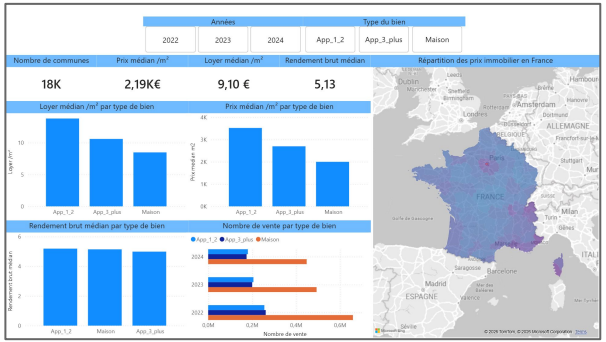

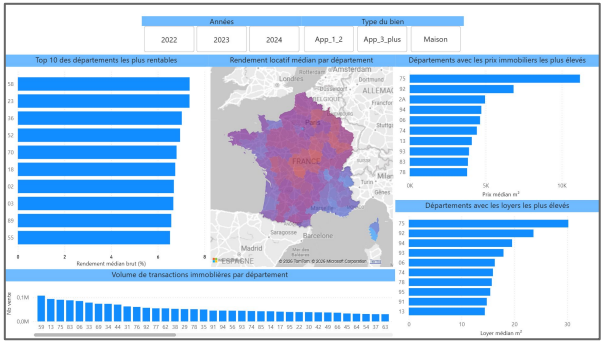

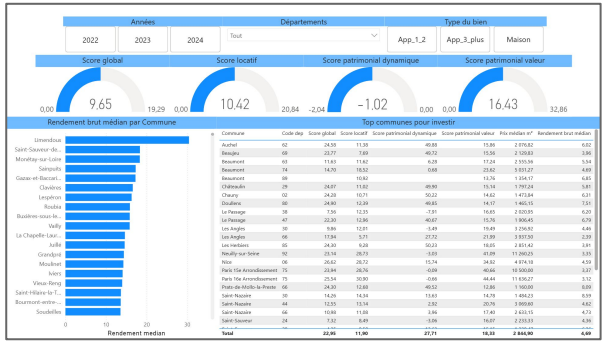

Vue d’ensemble du marché immobilier :

- indicateurs clés du marché
- distribution des prix et des rendements
- carte des prix immobiliers

Analyse territoriale :

- comparaison des départements
- carte des rendements locatifs
- analyse des loyers et des volumes de transactions

Opportunités d’investissement :

- classement des communes
- analyse des scores d’investissement
- identification des marchés attractifs

Conclusion

Principaux enseignements

L’analyse du marché immobilier français met en évidence :

- de fortes disparités territoriales
- un arbitrage entre rentabilité locative et valorisation patrimoniale
- des territoires présentant un potentiel d’investissement particulièrement attractif

Apports du projet

Ce projet démontre ma capacité à :

- manipuler et analyser de grandes bases de données
- croiser plusieurs sources de données publiques
- construire des indicateurs décisionnels
- développer un dashboard interactif d’aide à la décision

Perspectives d’amélioration

Plusieurs pistes pourraient enrichir l’analyse :

- intégration de données économique locales
- analyse de l’accessibilité et des transports
- développement de modèles prédictifs du marché immobilier